Manuel utilisateur du plugin « Assistant listes »
V0.0.1

Identifiant			Version	Date de création
			0.0.1	05/02/2026
Rédacteur	Gérôme PECHEUR			
Entité émettrice				
Diffusion	☐ Interne	■ Ouverte	☐ Limitée	
Résumé	Installation et utilisation du plugin			
Approbateur		Date d'approbation	05/02/2026	

Lecteur(s)	

Version	Date	Modifié par	Historique des modifications
0.0.1	05/02/2026	Gérôme PECHEUR	Création

Sommaire

1 PREREQUIS 2
2 RESUME 2
3 INSTALLATION 2
4 PRESENTATION DU GESTIONNAIRE DE LISTES 3
5 PRESENTATION D'UNE LISTE 4
6 CREATION DE LISTES 4
7 AJOUT D'ELEMENTS DANS UNE LISTE 4
7.1 Via : Sel -> liste 4
7.2 Via : « glissé & déposé » 4
7.2.1 D'une liste A vers la liste « sélection » : 4
7.2.2 De la liste « Sélection » vers une liste A 4
7.2.3 D'une liste A vers une liste B 4
8 SUPPRESSION D'ELEMENTS DANS UNE LISTE 5
8.1 Via le menu contextuel 5
8.2 Via : « glissé & déposé » 5
9 OUVERTURE DE LA TABLE ATTRIBUTAIRE 5

1 Prérequis

Version de QGIS : 3.40 ou supérieur.
Le plugin « maitre » doit être installé préalablement.

2 Résumé

Ce plugin permet de gérer des listes d'entités de géométries différentes (création, suppression)

3 Installation

Ouvrir QGIS.
Allez dans **Extensions/Installer/Gérer les extensions**, cliquez sur **Installer depuis un ZIP**, sélectionner le fichier ZIP puis cliquez sur **Installer le plugin**.

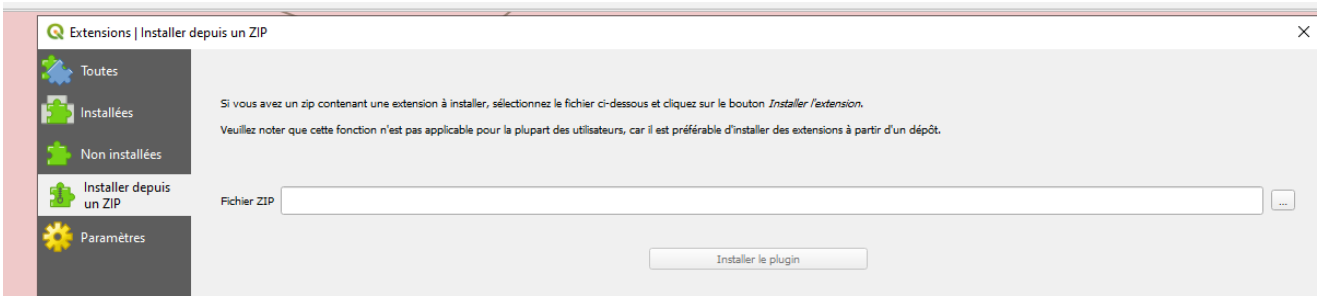

4 Présentation du gestionnaire de listes

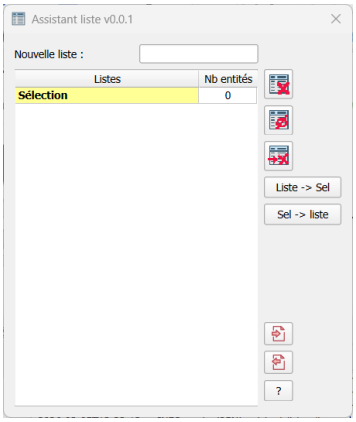

Par défaut ce gestionnaire de liste intègre une liste spéciale « Sélection »
Cette liste est mise à jour à chaque changement de sélection dans QGIS.

Nouvelle liste : : Création d'une nouvelle liste (renseigner un nom puis appuyer sur entrée)

: Suppression de toutes les listes

: Suppression de toutes les listes vides.

: Suppression de la liste sélectionnée.

Liste -> Sel : Sélection dans QGIS de toutes les entités de la liste sélectionnée.

Sel -> liste : Ajout dans la liste de toutes les entités sélectionnées dans QGIS.

: Importation d'une liste (identifiants ou cleabs)

: exporter la liste sélectionnée (le format peut être : identifiants ou cleabs)

? : A propos de … (historique des versions et visualisation de cette documentation)

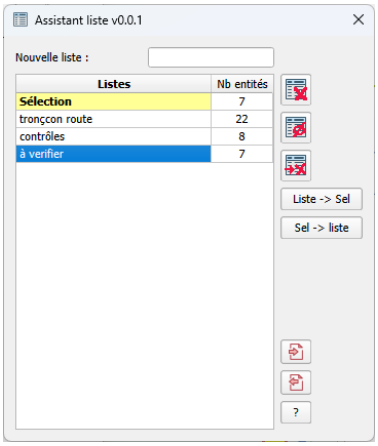

Gestionnaire configuré avec plusieurs listes.
Pour ouvrir une liste il faut faire un « double-clic » sur la liste désirée.

5 Présentation d'une liste

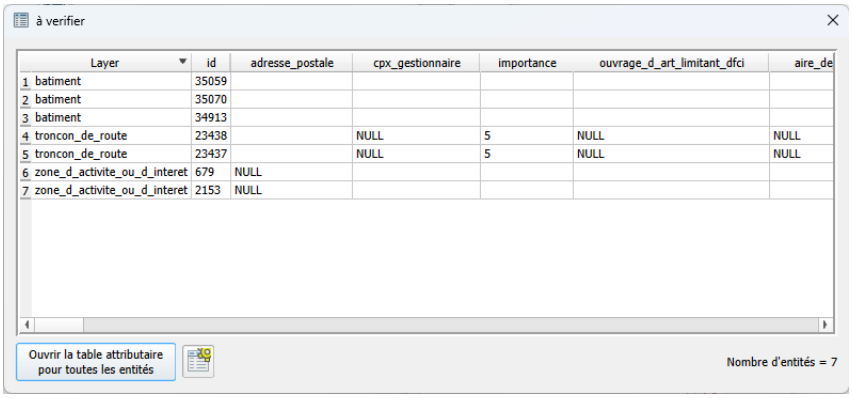

	Layer	id	adresse_postale	cpx_gestionnaire	importance	ouvrage_d_art_limitant_dfci	aire_de
1	batiment	35059					
2	batiment	35070					
3	batiment	34913					
4	troncon_de_route	23438		NULL	5	NULL	NULL
5	troncon_de_route	23437		NULL	5	NULL	NULL
6	zone_d_activite_ou_d_interet	679	NULL				
7	zone_d_activite_ou_d_interet	2153	NULL				

6 Création de listes

La nouvelle liste ne doit pas se nommer « Sélection » ni être déjà présente dans le gestionnaire.

7 Ajout d'éléments dans une liste

7.1 Via : Sel -> liste

Ajoute dans la liste toutes les entités sélectionnées dans QGIS (le contenu de la liste est vidée avant ajout)

7.2 Via : « glissé & déposé »

On peut effectuer un « glisser & déposé » de lignes d'une liste vers une autre liste.
On peut sélectionner plusieurs lignes.

7.2.1 D'une liste A vers la liste « sélection » :

- Une ou plusieurs lignes sont ajoutées à la liste « Sélection », les entités correspondantes sont également ajoutées à la sélection de QGIS.
- La liste « A » n'est pas modifiée (la ou les lignes de la liste d'origine ne sont pas supprimées).

7.2.2 De la liste « Sélection » vers une liste A

- Une ou plusieurs lignes sont ajoutées à la liste « A »
- La liste « Sélection » n'est pas modifiée.

7.2.3 D'une liste A vers une liste B

- La ou les ligne sont supprimées de la liste « A »
- La ou les ligne sont ajoutées de la liste « B »

8 Suppression d'éléments dans une liste

8.1 Via le menu contextuel

- On sélectionne une ou plusieurs lignes d'une liste
- Un « clic droit » fait apparaitre un menu contextuel :

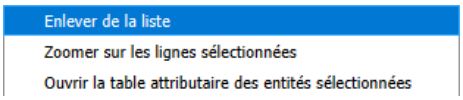

Cas de la liste « Sélection » :

- La ou les lignes sont supprimées de la liste et la sélection dans QGIS est actualisée ;

Cas d'une liste quelconque :

- La ou les lignes sont supprimées de la liste

8.2 Via : « glissé & déposé »

Le glissé & déposé de la liste « A » vers la liste « B » ajoute les lignes dans la liste « B » et supprime les lignes dans la liste « A »

9 Ouverture de la table attributaire

Via le menu contextuel il est possible d'ouvrir la table attributaire QGIS correspondant à la ligne sélectionnées (= entités)

Si plusieurs lignes correspondent à des entités appartenant à différentes couches, une table attributaire sera ouverte pour chaque couche.